Propuesta de servicios

Municipalidad de Estación Central

Gobernanza, fiscalización y gestión territorial de redes de telecomunicaciones

Implementación comunal de instrumentos normativos, territoriales y procedimentales para la identificación, ordenación, mantención y retiro de líneas y elementos de redes de telecomunicaciones en bienes nacionales de uso público.

Mandante	Ilustre Municipalidad de Estación Central.
Plazo referencial	16 semanas prorrogables a solicitud de mandante.
Monto total del servicio	$31.000.000

Quiénes somos y qué hacemos

Quiénes somos	Coordenadas Públicas es una firma especializada en asuntos públicos, regulación sectorial y entorno territorial. Su trabajo se orienta a traducir marcos normativos y desafíos institucionales en instrumentos concretos de gestión para instituciones públicas y privadas.
Qué hacemos	Apoyamos a municipios y organismos públicos en el diseño de ordenanzas, revisión normativa, catastros focalizados, matrices de riesgo, protocolos de fiscalización, tableros de seguimiento y hojas de ruta de implementación. El objetivo es dejar capacidades e instrumentos utilizables por la administración municipal.

Marzo de 2026

1. Presentación de la propuesta

Coordenadas Públicas presenta a la Municipalidad de Estación Central la siguiente propuesta de servicios para apoyar la implementación comunal del marco vigente aplicable a la identificación, ordenación, mantención y retiro de líneas y elementos de redes de telecomunicaciones emplazados en bienes nacionales de uso público.

La propuesta se formula considerando las características territoriales de la comuna, la necesidad de contar con instrumentos administrativos utilizables por el municipio y la conveniencia de abordar esta materia mediante una solución institucional, jurídicamente sólida y económicamente razonable.

2. Antecedentes de Estación Central

Estación Central presenta condiciones territoriales que justifican una intervención específica en esta materia. Se trata de una comuna de 15,0 km^2, con una población estimada al año 2024 de 181.049 habitantes, alta densidad de ocupación y predominio de tendido aéreo. A ello se suma una estructura urbana mixta, donde conviven áreas residenciales, corredores de movilidad, equipamientos y sectores de fuerte actividad comercial.

En este contexto, el desorden del cableado no constituye solo un problema visual. También incide en el entorno urbano, multiplica reclamos ciudadanos, complejiza la gestión municipal y hace necesario contar con criterios claros para priorizar, documentar y activar acciones de fiscalización y seguimiento.

Antecedente comunal	Implicancia para el municipio
Alta densidad y uso intensivo del espacio público	Se requiere priorización por criticidad y un tratamiento territorial focalizado.
Predominio de tendido aéreo	Es necesario levantar evidencia técnica y consolidar expedientes de respaldo.
Comuna con áreas residenciales y ejes de actividad comercial	La fiscalización y el seguimiento deben diferenciar polígonos y niveles de exposición.
Volumen relevante de reclamos y multiplicidad de actores	Se necesita un flujo interno claro entre detección, validación, requerimiento y seguimiento.

3. Objeto del servicio

El servicio tiene por objeto apoyar a la Municipalidad de Estación Central durante un período referencial de 16 semanas en la preparación e instalación de instrumentos concretos para gestionar esta materia. El alcance considera la revisión del marco comunal aplicable, la elaboración de una nueva ordenanza o adecuación normativa, el diseño de herramientas de fiscalización, un catastro focalizado de puntos críticos, la definición de protocolos internos de trabajo y la capacitación de equipos municipales.

La propuesta no considera la contratación de una cuadrilla ni la compra de vehículos. El foco está puesto en fortalecer la capacidad municipal instalada y reestructurar los flujos de proceso para facilitar el cumplimiento de la normativa local.

4. Servicios comprendidos en la propuesta

4.1 Diagnóstico y adecuación normativa

Se revisará el marco sectorial y comunal aplicable al caso de Estación Central, identificando competencias municipales, criterios de exigibilidad, soportes procedimentales y materias que requieran ser aterrizadas en un instrumento local.

- Revisión del marco vigente y levantamiento de antecedentes comunales relevantes.
- Elaboración de nueva ordenanza o adecuación normativa, según corresponda.
- Jornada de trabajo con autoridades y concejalías.
- Jornadas de difusión y trabajo con la comunidad.
- Diseño de matriz infraccional y criterios de aplicación.
- Preparación de formatos y actos administrativos tipo para respaldo de la gestión municipal.

Producto principal: Ordenanza o adecuación normativa, matriz infraccional y set básico de formatos administrativos.

4.2 Catastro territorial focalizado y priorización

Se realizará un levantamiento focalizado de puntos críticos en polígonos definidos con la contraparte municipal. El trabajo considerará clasificación por criticidad, exposición y prioridad territorial, con soporte técnico para el seguimiento posterior.

- Definición conjunta de polígonos prioritarios y criterios de observación.
- Levantamiento de puntos críticos y elaboración de fichas por caso.
- Priorización territorial según criticidad y exposición.
- Consolidación de base georreferenciada y visor de gestión de elementos de red y basura aérea en tiempo real

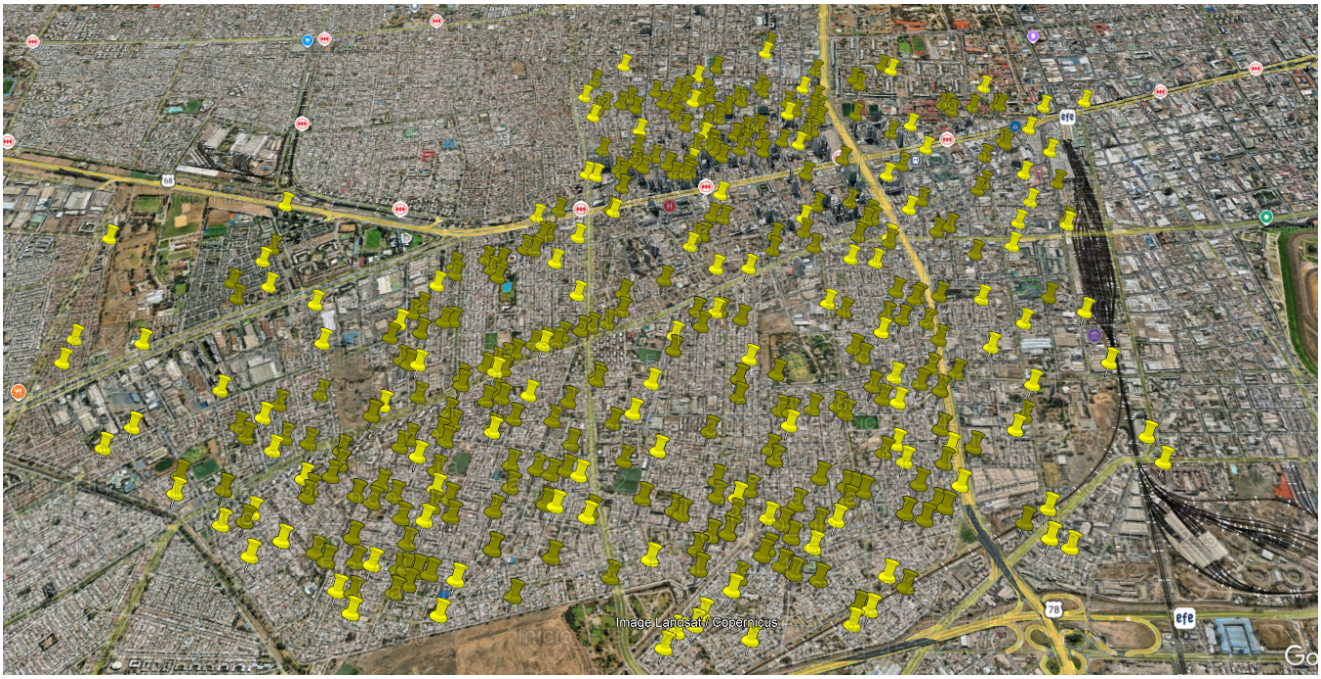

Levantamiento actual de elementos de red que se encuentren en desuso o basura aérea.

Propuesta de visor comunal:

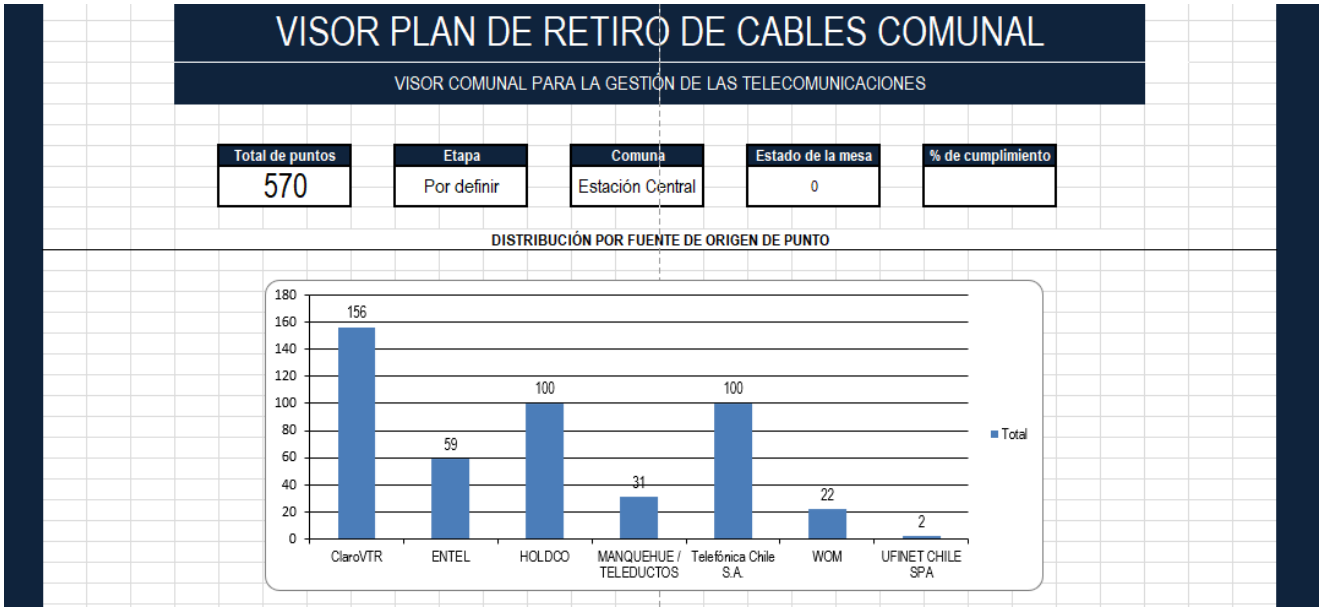

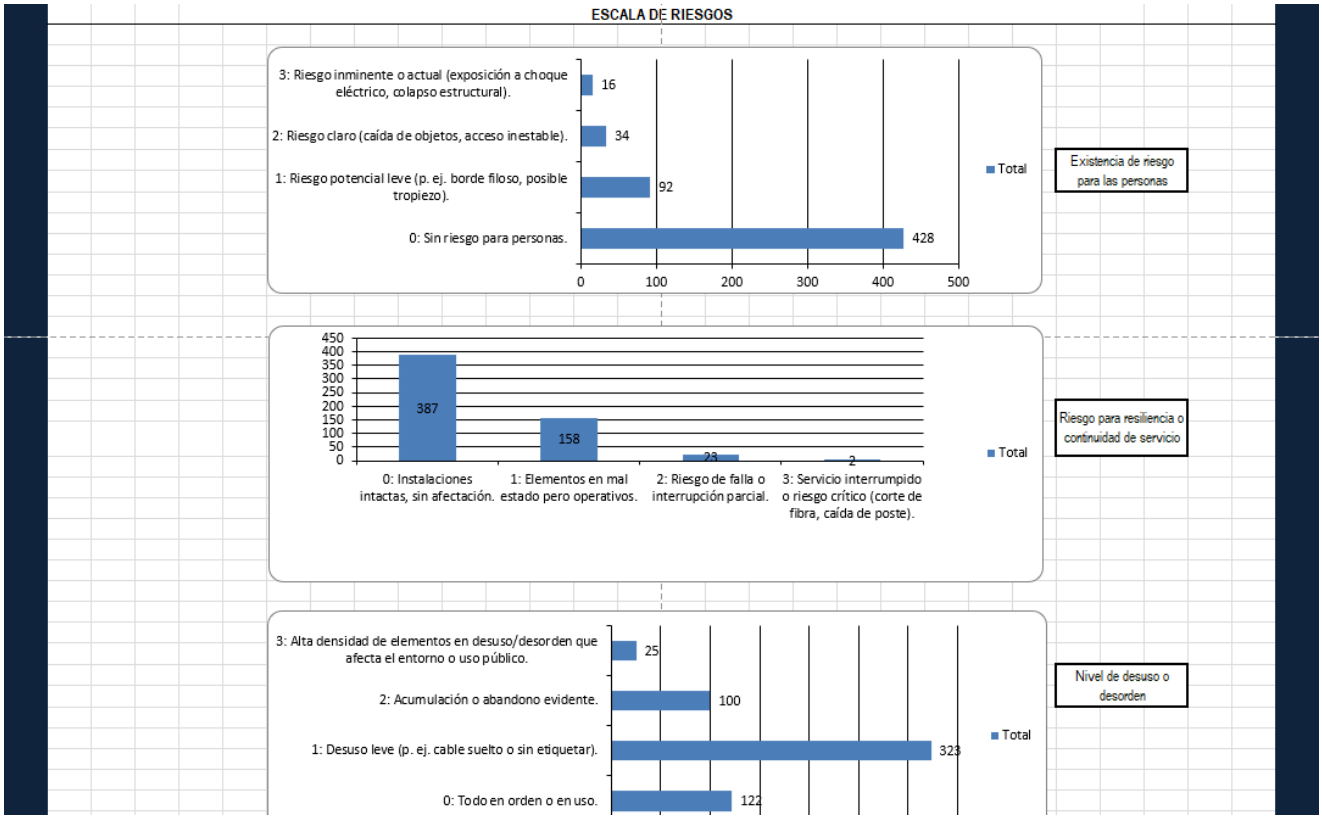

Producto principal: catastro territorial georreferenciado y focalizado, fichas de respaldo y matriz de priorización para la toma de decisiones..

4.3 Protocolos internos, expedientes y seguimiento

Se diseñará un flujo de trabajo interdirecciones para que las detecciones en terreno puedan transformarse en antecedentes útiles para requerimiento, fiscalización y seguimiento, reduciendo dispersión interna y mejorando trazabilidad.

- Definición de roles entre contraparte municipal, inspección, jurídica y áreas de apoyo.
- Estandarización de registros, evidencia y formatos de expediente.
- Creación canales de comunicación acorde a normativa SUBTEL vigente.
- Diseño de protocolo de derivación, revisión y seguimiento.
- Preparación de tablero inicial de seguimiento para uso interno.

Producto principal: protocolo interno de trabajo, formatos de expediente y tablero inicial de seguimiento.

4.4 Capacitación y acompañamiento de implementación

Se realizará una etapa final de transferencia y validación para que los instrumentos preparados puedan ser utilizados por el municipio con criterios comunes y una hoja de ruta de implementación inmediata.

- Jornadas de capacitación aplicada a equipos municipales.
- Revisión final de instrumentos y ajustes de consistencia.
- Acompañamiento en la puesta en marcha inicial del modelo de trabajo.
- Elaboración de informe de cierre y hoja de ruta de implementación.

Producto principal: material de capacitación, validación final e informe de cierre con hoja de ruta.

5. Forma de ejecución

La ejecución considera una secuencia de trabajo de 16 semanas, con validaciones parciales con la contraparte municipal. El calendario puede ajustarse según disponibilidad de información, definiciones internas del municipio y priorización territorial.

Fase	Semanas	Contenido
Fase 1	1 a 4	Revisión de antecedentes, levantamiento inicial, definición de alcance y priorización con la contraparte municipal.
Fase 2	3 a 10	Desarrollo de la propuesta normativa, matriz infraccional, catastro focalizado y fichas territoriales.
Fase 3	7 a 13	Diseño de protocolos internos, expedientes de fiscalización, tablero inicial y proceso de validación.
Fase 4	12 a 16	Capacitación, ajustes finales, informe de cierre y hoja de ruta de implementación.

Carta Gantt referencial - 16 semanas

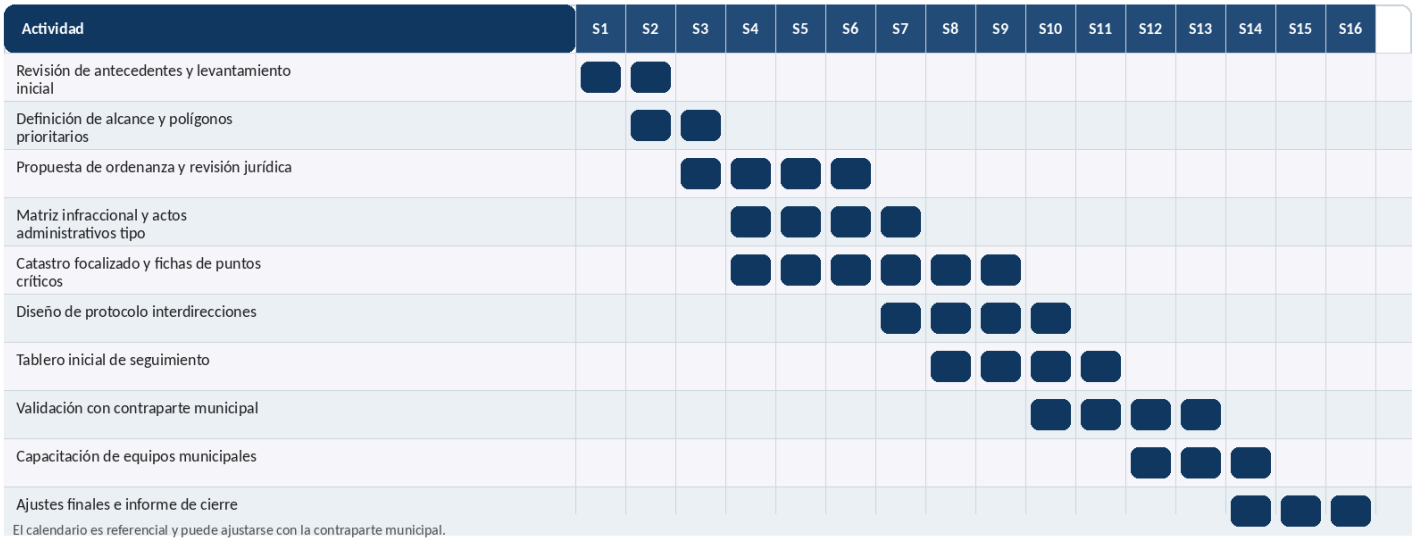

Carta Gantt referencial de 16 semanas.

6. Marco normativo considerado

El servicio se desarrollará considerando, entre otras, las siguientes bases normativas. La revisión específica del articulado, de los procedimientos y de las competencias aplicables se ajustará al texto vigente al momento de la contratación y a las particularidades del caso comunal.

La finalidad de este componente es traducir el marco sectorial y la potestad reglamentaria comunal en un instrumento de aplicación práctica para la Municipalidad de Estación Central, con soportes claros para revisión, requerimiento y seguimiento.

Norma o fuente	Materia relevante	Aplicación dentro del servicio
Ley N° 18.168, General de Telecomunicaciones	Marco sectorial aplicable a redes e infraestructura de telecomunicaciones.	Se considera como base para la revisión jurídica y la adecuación del instrumento comunal.
Ley N° 21.172	Modificaciones relevantes en materia de identificación, mantención, ordenación y retiro de elementos de red.	Sirve de referencia para el diseño de exigencias, obligaciones y soportes de gestión comunal.
Decreto N° 176	Plan de gestión y mantención aplicable a líneas aéreas y subterráneas.	Orienta la construcción del enfoque operativo y de los antecedentes técnicos del servicio.
Normativa técnica e instrucciones complementarias de Subtel	Criterios, formatos y exigencias técnicas vinculadas a información y gestión del sistema.	Se incorpora al diseño de fichas, expedientes y soportes técnicos de seguimiento.
Ley N° 18.695 y potestad reglamentaria comunal	Facultades municipales para ordenar su gestión interna, dictar ordenanzas y activar fiscalización dentro de sus competencias.	Permite aterrizar el marco sectorial a un instrumento y procedimiento de aplicación local.

7. Entregables para la Municipalidad

Como resultado del servicio, se contempla la entrega de los siguientes productos de trabajo:

- Informe de diagnóstico comunal y revisión normativa inicial.
- Nueva ordenanza o adecuación normativa municipal.
- Matriz infraccional y formatos administrativos de apoyo.
- Catastro focalizado de puntos críticos y fichas territoriales.
- Protocolo interdirecciones y formatos de expediente de fiscalización.
- Tablero inicial de seguimiento para uso interno.
- Jornadas de capacitación para equipos municipales.
- Informe final con ajustes y hoja de ruta de implementación.
- Memoria de procesos de participación ciudadana.
- Visor comunal para la toma de decisión de autoridades.

8. Oferta económica

El monto total propuesto para la ejecución del servicio asciende a $31.000.000. La distribución referencial del presupuesto por componente es la siguiente:

Componente	Monto
Diagnóstico comunal y revisión normativa inicial	$ 5.000.000
Nueva ordenanza, matriz infraccional y actos tipo	$ 7.000.000
Catastro focalizado y priorización territorial	$ 9.000.000
Protocolos, expedientes de fiscalización y tablero de seguimiento	$ 6.000.000
Capacitación, acompañamiento de implementación e informe final	$ 4.000.000
Total	**$ 31.000.000**

9. Consideraciones de ejecución

- La propuesta considera la designación de una contraparte municipal para efectos de coordinación y validación.
- El alcance territorial del catastro será focalizado y se definirá en conjunto con el municipio al inicio del servicio.
- El calendario es referencial y puede ajustarse según disponibilidad de información y procesos internos de revisión.
- La revisión específica del articulado aplicable se efectuará sobre el texto vigente al momento de la contratación.
- El tratamiento tributario definitivo deberá revisarse de acuerdo con la modalidad de contratación aplicable.
- Incorpora relacionamiento y jornadas de trabajo con autoridades, juntas vecinales y sociedad civil.

La presente propuesta busca dejar a la Municipalidad de Estación Central con un conjunto de instrumentos concretos para gestionar esta materia, con respaldo normativo, soporte territorial y una secuencia de implementación administrativamente viable.